القضية التنفيذية رقم 75 / 2026 انابات
محكمة بداية شرق عمان

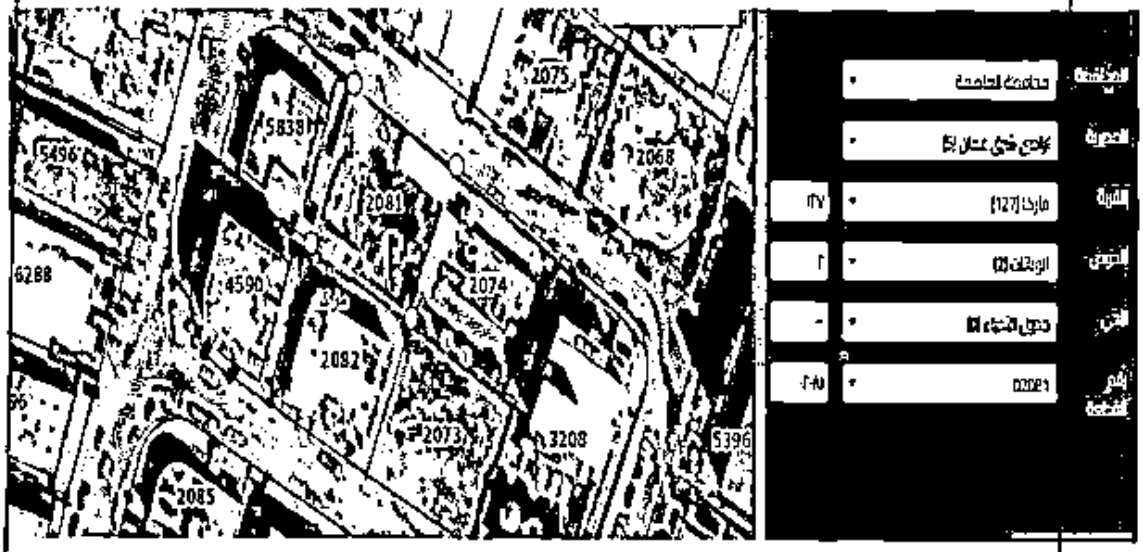

القطعة	الحوض	لوحة	القرية	مديرية التسجيل
2081	2 الونانات	0	ماركا	شرق عمان

1

تقدير قيمة

رقم القضية/الدعوى	2026/75 انابات
تاريخ الكشف	2026/3/25

بناة على قراركم بأنتخابي انا المهندس مجدي الاقطش خبيرا في القضية التنفيذية أعلاه لوضع اليد وتقدير قيمة القطعة ووصفها وصفا دقيقا وشاملا والخدمات التي تصلها وكذلك لبيان الاسس والمعايير التي تم الاعتماد عليها في تقديرسعر المتر المربع الواحد، فقد قمت بالكشف الحسي على رقبة العقار وبرفقة موظف تنفيذ محكمة شرق عمان ، وبعد تحلفي القسم القانوني للقيام بالمهمة الموكولة الي بكل امانة وإخلاص قمت باجراء الكشف الحسي وعلى رقبة العقار وبعد افهامي المهمة الموكولة الي وكذلك تم التأكد من مطابقة مبرزات القضية من سند تسجيل ومخطط اراضي ومخطط تنظيمي فوجدت مطابقة وتبين لي مايلي:-

معلومات القطعة

القطعة	الحوض	لوحة	القرية	مديرية التسجيل
2081	2 الونانات	0	ماركا	شرق عمان

الهدف من التقرير

طالب التقدير	الهدف منه
دائرة تنفيذ محكمة شرق عمان	القيمة السوقية

بالرجوع الى سجلات دائرة الاراضي تبين ان القيمة الادارية للقطعة بمبلغ 110 دينار

وصف الموقع العام

تقع القطع اعلاه في ماركا الونانات ضمن منطقة صناعية حيث تبعد القطعة الى الشمال الغربي من جسر ماركا بحدود 480 متر والى الغرب من شارع الملك حسين بحدود 500 متر والى الشمال من شارع الجيش بحدود 290 متر والى الشرق من مصنع رومو انترناشونال بحدود 240 متر

جميع الخدمات متوفرة حيث تقع القطعة الى الشمال الغربي من قاعات نيوجرسي للاحتفالات بحدود 250 متر والى الشمال الشرقي من مصنع الكسيح بحدود 500 متر بالقرب من مؤسسة ليان للكيماويلت ومنظفات نانا

القطعة حسب تنظيم امانة عمان منظمة صناعات متوسطة بأحكام خاصة وتقع على شارع معبد شمال القطعة وهو بعرض 12 متر وبطول واجهة للقطعة على الشارع بحدود 32 متر وبعمق تقريبي 30 متر

شكل القطعة منتظم والقطعة شبه مستوية مع وجود ميل خفيف بأتجاه الجنوب الشرقي

وهي محاطة بالاسوار من الجهات الاربعة مع وجود مدخل كراج بدون بوابة مختلف الارتفاعات

والقطعة تحمل ترقيم امانة 4 وذلك حسب امانة عمان

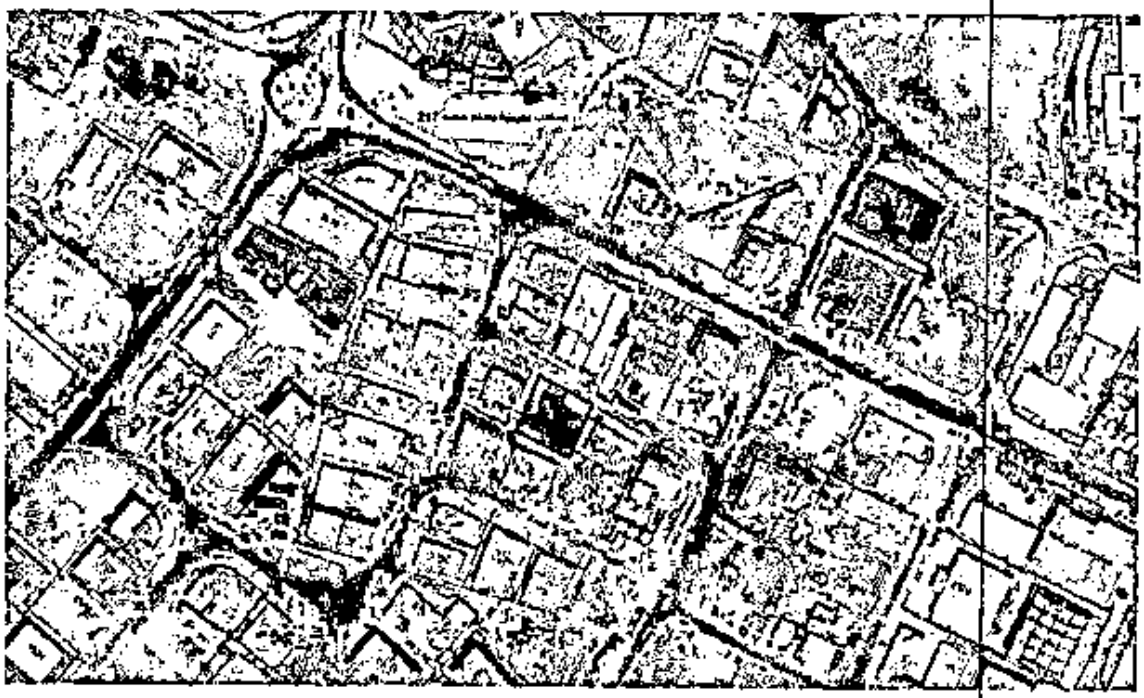

صور للعقار



احتساب القيمة العقارية

وعليه وبعد الاستئناس بالقيمة الادارية في دائرة الاراضي والرجوع للتقديرات الحقيقية في الواقع أقدر قيمة المتر الواحد للارض بعد الاخذ بعين الاعتبار قربها وبعدها عن الخدمات وغيرها من المؤثرات التي تؤثر على القيمة بمبلغ 150 دينار

150 * 961 = 144150 دينار

وعليه تكون القيمة الاجمالية للارض وما عليها بمبلغ 144150 دينار

مائة واربعة واربعون الفا ومائة وخمسون دينار

أقر انا الخبير ادناه مايلي:
حسب نص المادة رقم (83-3) انني افصح عن عدم وجود ايه ظروف او اسباب من شأنها اثارة الشكوك حول حيادتي واستقلالي عن اي من اطراف الدعوى او وكلائهم او هئية المحكمة
وأصرح انني قمت بأعداد التقرير لوحدي وبدون مساعدة اي شخص اخر وانني مؤهل للقيام بالمهمة الموكولة الي
قمت بالاعتماد على خبرتي كمقدر عقاري ومهندس ومعتمد وقمت بالاعتماد على موقع العقار وتنظيمه ومساحته وشكله وطبيعته وبعده وقربه من الخدمات والمناطق السكنية والتجارية ونوعية التشطيبات في الاستنتاجات التي توصلت اليها في التقرير
وتم الاعتماد على الوثائق المسلمة الي من المحكمة ولم يتم تسليمي او الاعتماد على اي من الوثائق غير المودعة لدى المحكمة
تم التوصل الى النتيجة بالاعتماد على خبرتي كمقدر عقاري ومهندس معتمد وعلى دراية وعلم بالاسعار في المنطقة وبالاعتماد على المساحة والموقع والتنظيم والخدمات والتشطيبات والشكل والاستئناس باسعار المنطقة واسعار الاساس في دائرة الاراضي والمساحة وأؤيد ما جاء في تقريري من اراء واستنتاجات
وهذه حدود خبرتي أقدمها لمحكمتكم الموقرة حسب الاصول تحريرا بتاريخ 2026/3/29

الخبير المقدر
المهندس مجدي الاقطش

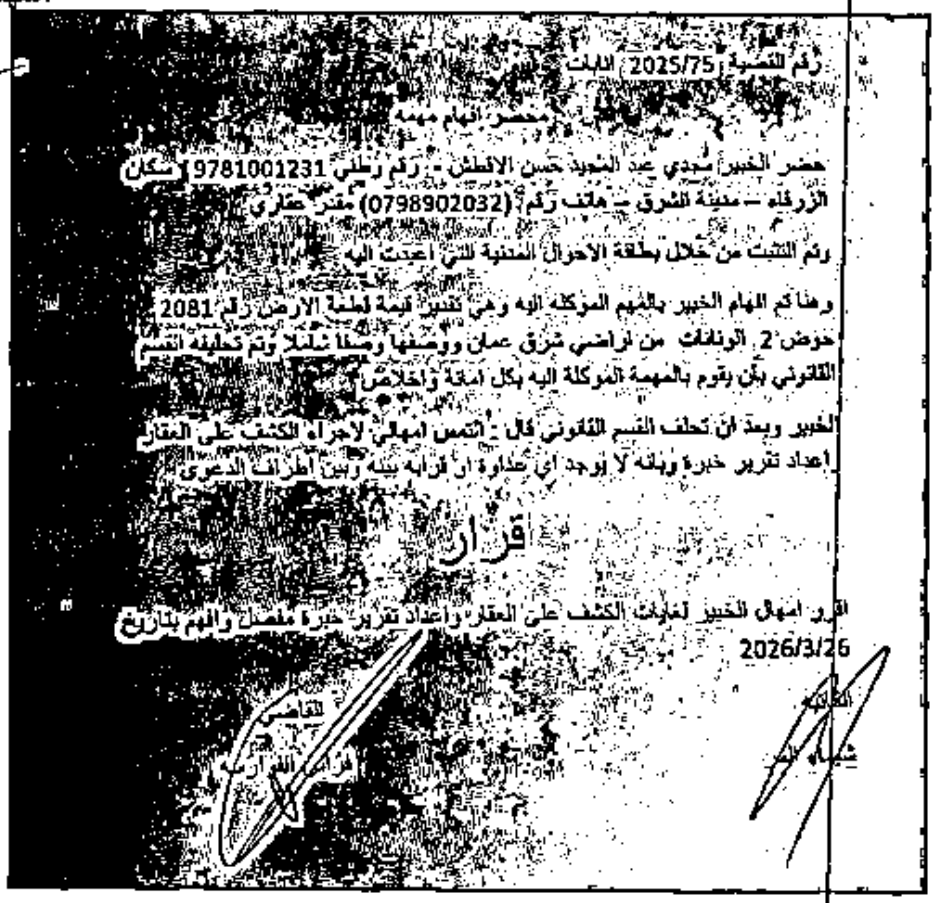
رقم القضية 2025/75 الدائرة
محضر انهاء مهمه
حضر الخبير مجدي عبد المجيد حسن الاقطش - رقم وطني 9781001231 سكان الزرقاء – مدينة الشرق – هاتف رقم (0798902032) مقدر عقاري
وتم التثبت من خلال بطاقة الاحوال المدنية التي ابرزت اليه
وهنا تم الهام الخبير بالمهم الموكله اليه وهي تقدير قيمة لمطعة الارض رقم 2081 حوض 2 الرمانات من اراضي شرق عمان ووصفها وصفا شاملا وتم تحليفه القسم القانوني بأن يقوم بالمهمة الموكلة اليه بكل امانة وإخلاص
الخبير وبعد ان تحلف القسم القانوني قال : التمس امهالي لاجراء الكشف على العقار واعداد تقرير خبرة وبانه لا يوجد اي عداوة او قرابه بينه وبين اطراف الدعوى
قرار
قرر امهال الخبير لغايات الكشف على العقار واعداد تقرير خبرة مفصل وافهم بتاريخ 2026/3/26
القاضي
الكاتب

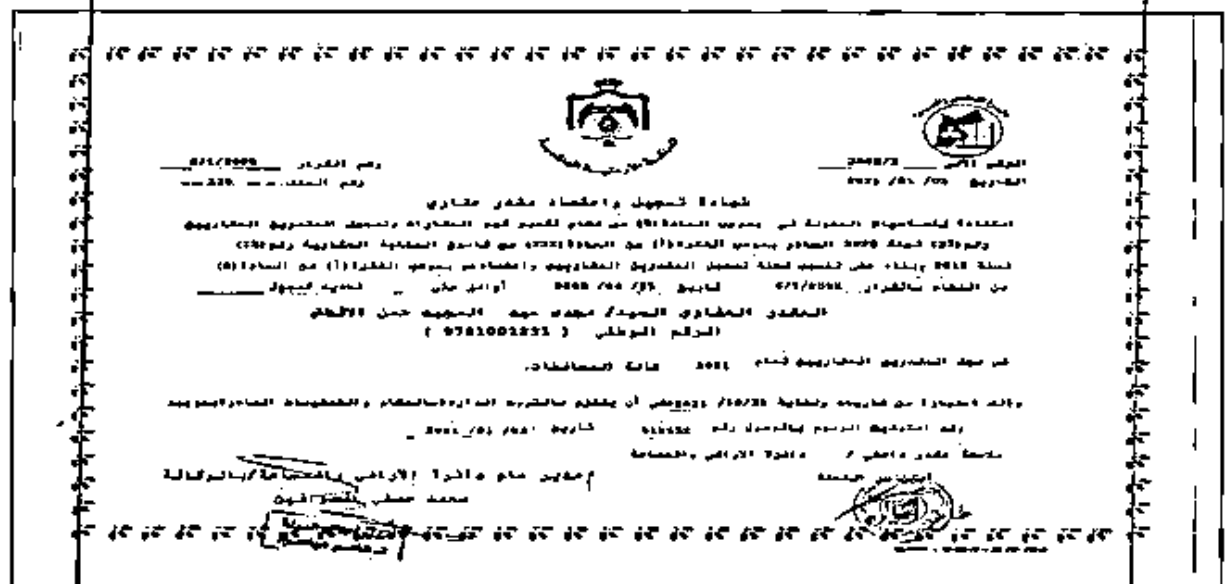

شهادة تسجيل واعتماد مقدر عقاري

المقدر العقاري السيد/ مهدي عبد السيد حسن الالفي

الرقم الوطني (9781001231)